توزيع استخدامات الاراضي مركز خارجة عام 2025

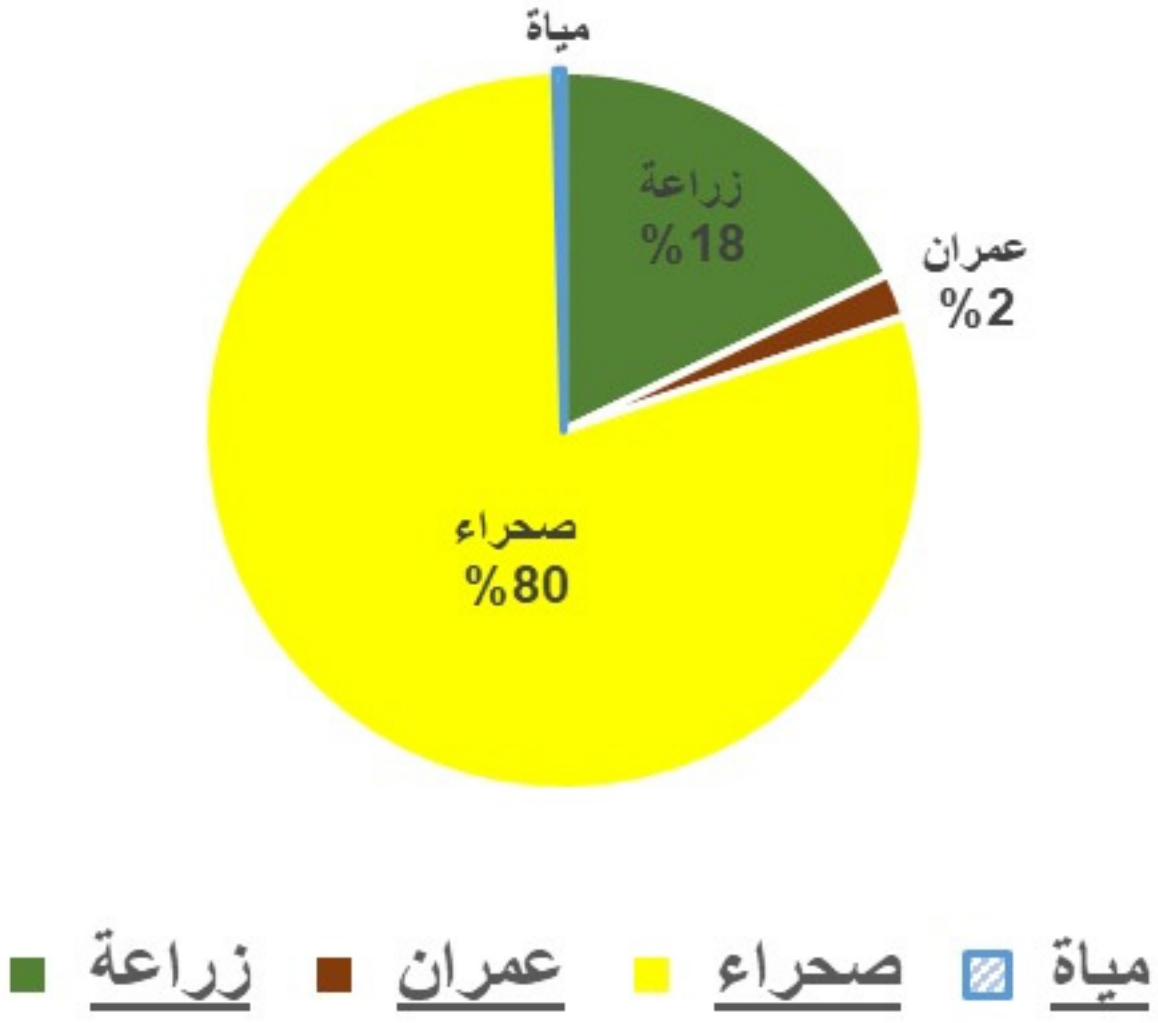

توزيع استخدامات الأراضي مركز الخارجة عام 2020

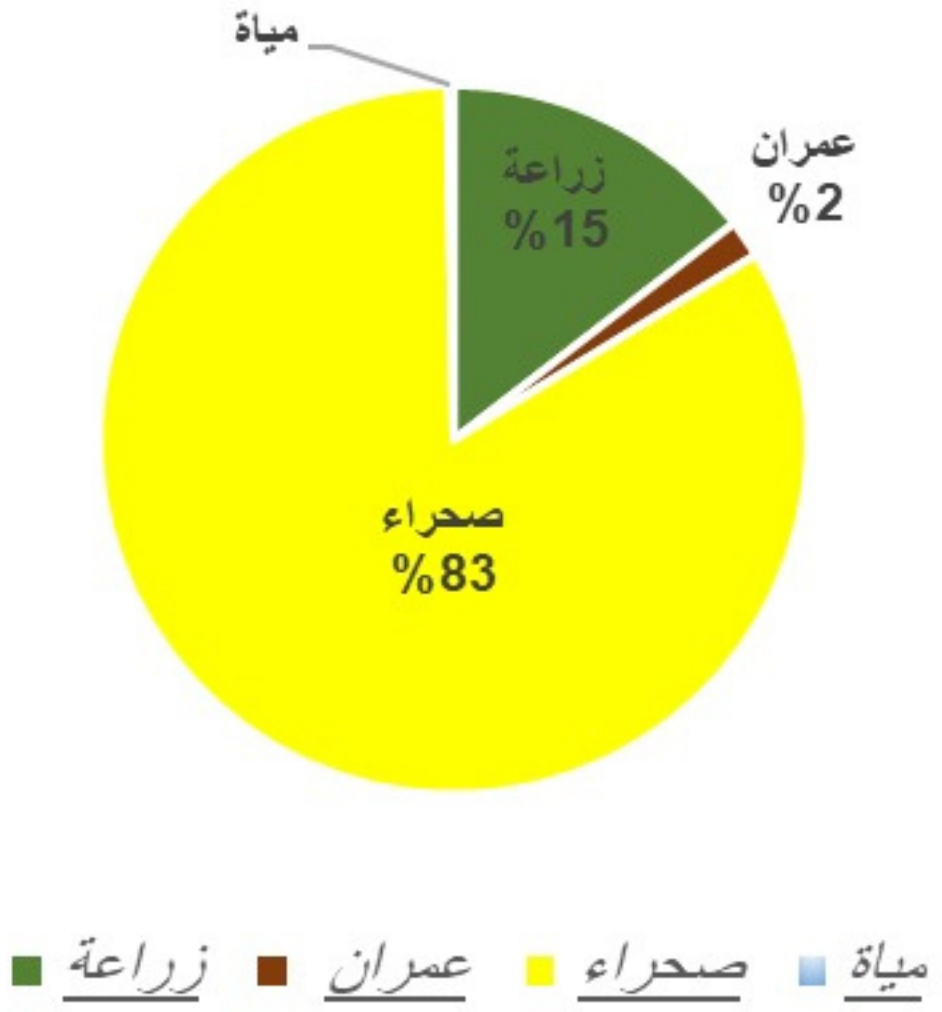

توزيع استخدامات الأراضي مركز خارجة عام 2010

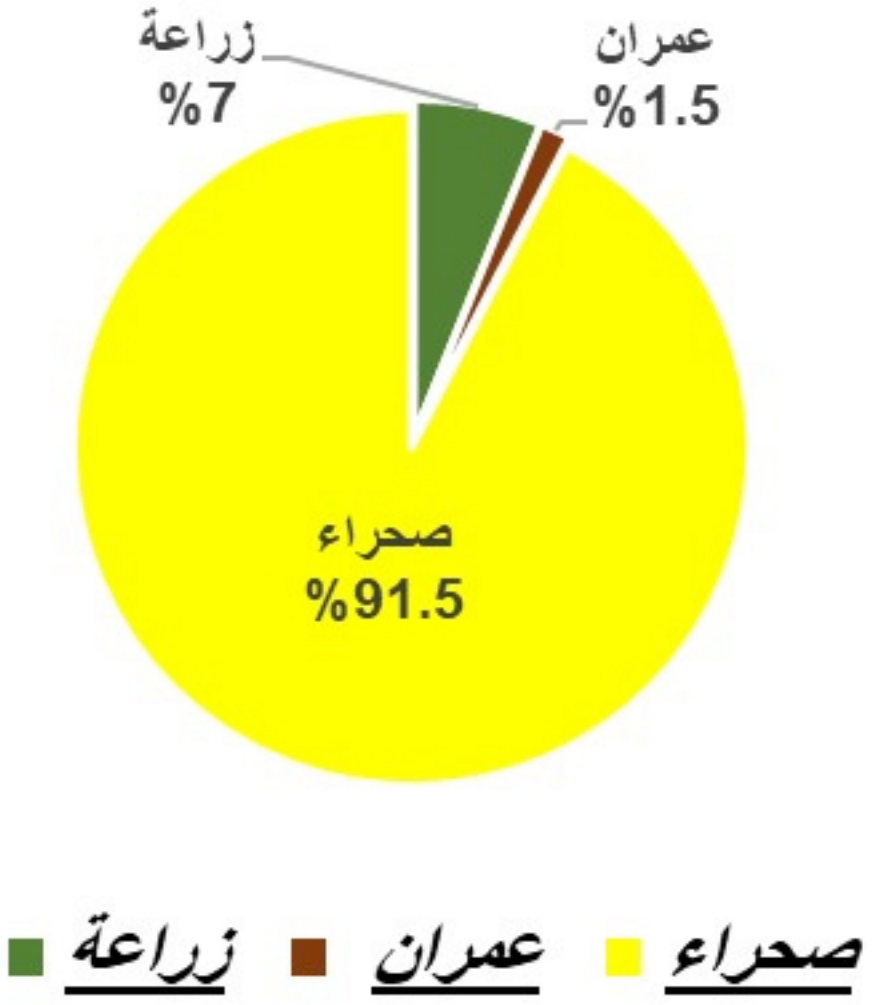

توزيع استخدامات الاراضي مركز الخارجة عام 2015

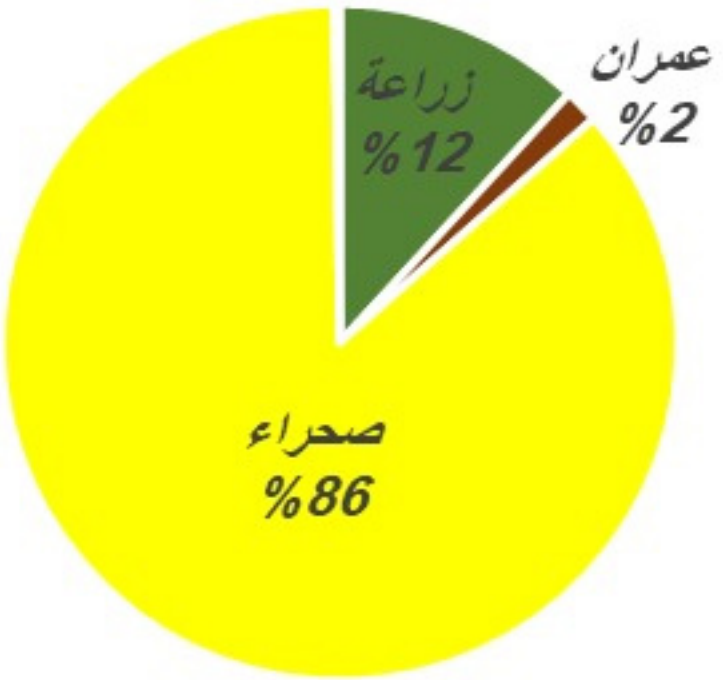

زراعة ■ عمران ■ صحراء ■ مياة ■

خريطة توزيع استخدامات الاراضي مركز خارجة عام 2000

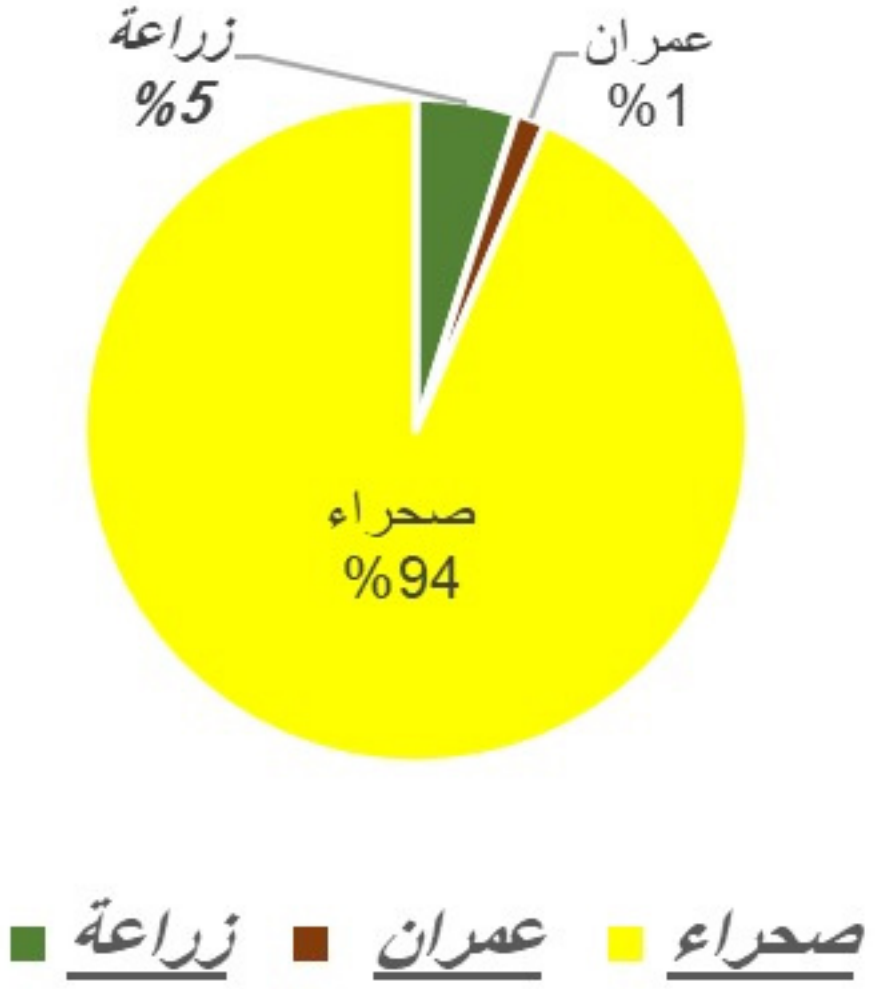

توزيع استخدامات الاراضي مركز خارجة عام 2005

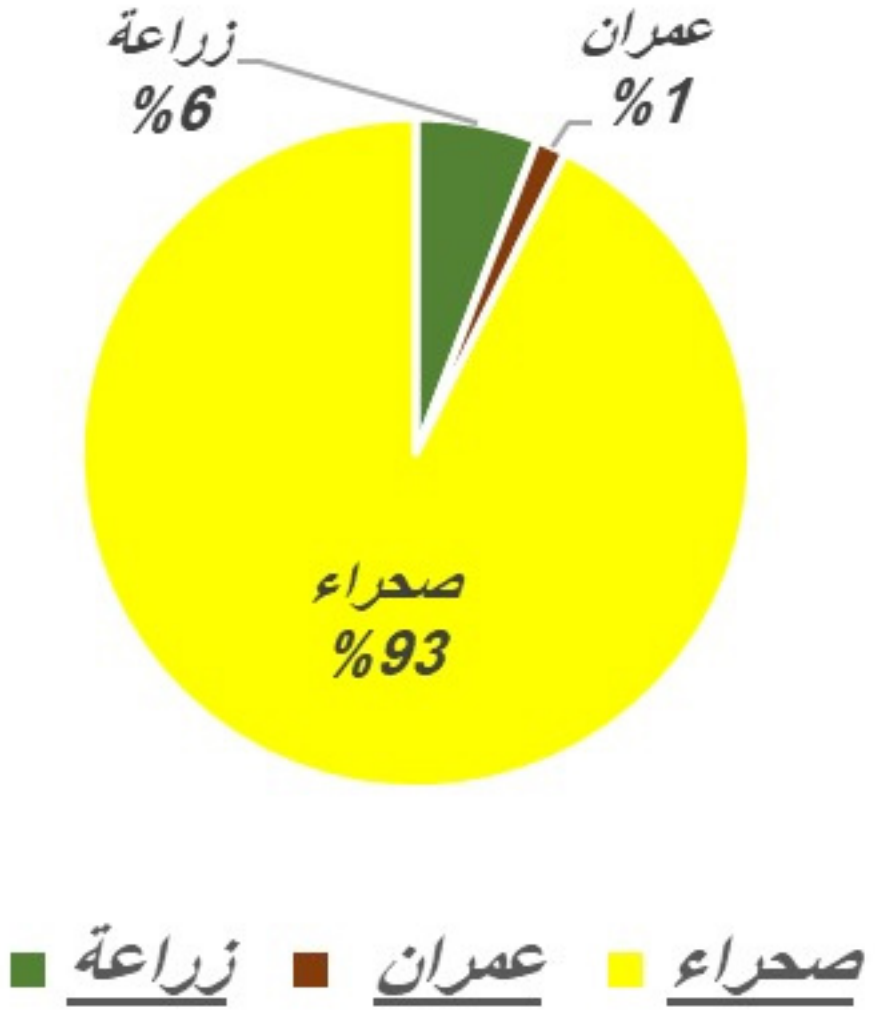

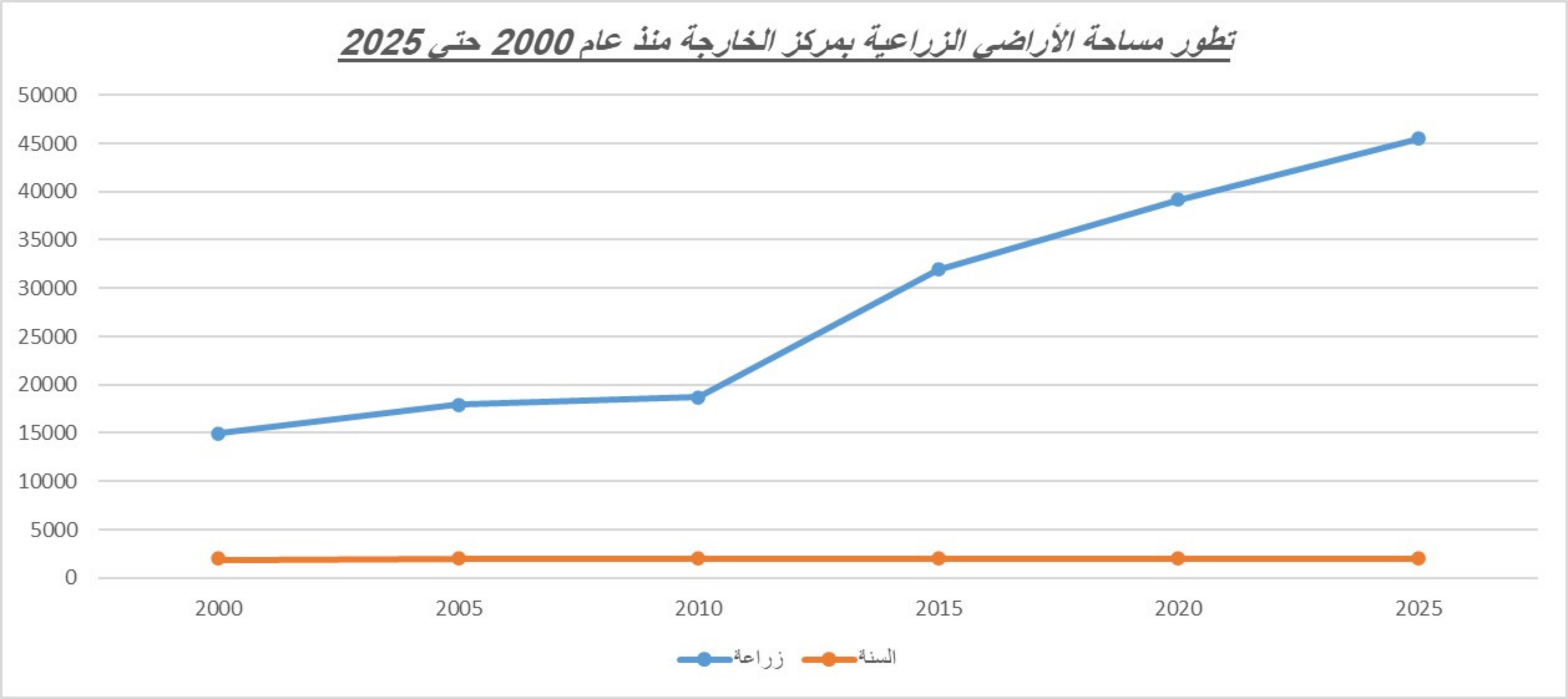
تطور مساحة الأراضي الزراعية بمركز الخارجة منذ عام 2000 حتى 2025
50000
45000
40000
35000
30000
25000
20000
15000
10000
5000
0
2000
2005
2010
2015
2020
2025
زراعة
السنة

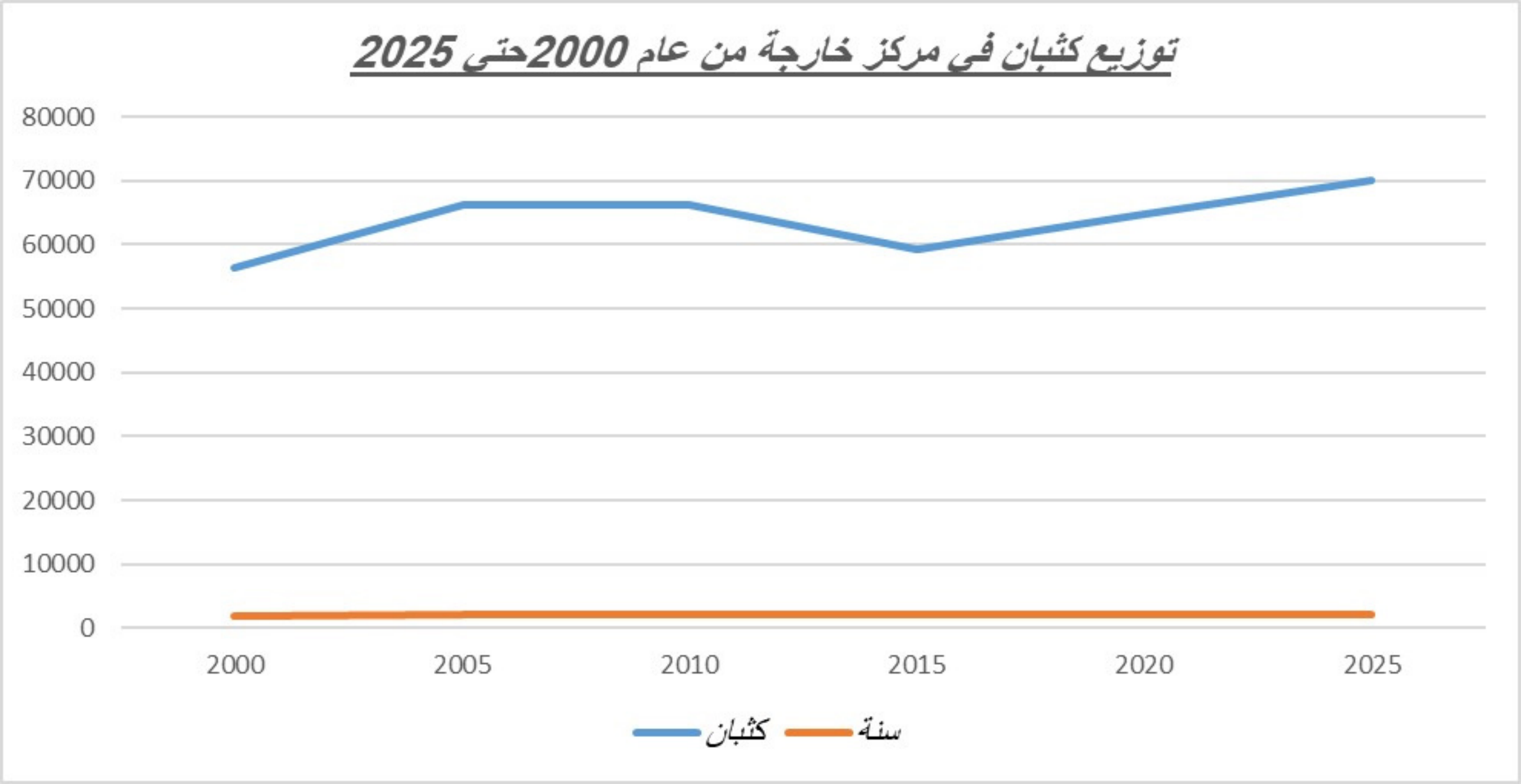
توزيع كثبان في مركز خارجة من عام 2000حتى 2025
80000
70000
60000
50000
40000
30000
20000
10000
0
2000
2005
2010
2015
2020
2025
كثبان
سنة

سنة	المساحة بالفدان	المساحة km2	الحالة جغرافية
2000	56302	236.4	بداية رصد
2005	66181	277.9	زيادة تدريجية
2010	66181	277.9	ثبات استقراري
2015	59349	249.4	تراجع موقت
2020	64810	272.2	عودة نشاط
2025	70000	301.5	اقصي زيادة

نوع تصنيف	النسبة المئوية	المساحة بالفدان عام 2000
زراعة	5%	13474
صحراء	94%	253311
عمران	1%	2695
اجمالي مساحة		269480

نوع تصنيف	النسبة المئوية	المساحة بالفدان عام 2010
زراعة	7%	18864
صحراء	91.5%	246574
عمران	1.5%	4042
اجمالي مساحة		269480

	نوع تصنيف	النسبة المئوية	المساحة بالفدان عام 2005
	زراعة	6%	16169
	صحراء	93%	250616
	عمران	1%	2695
	اجمالي مساحة		269480

	نوع تصنيف	النسبة المئوية	المساحة بالفدان عام 2020
	زراعة	15%	40422
	صحراء	83%	223668
	عمران	2%	5390
	اجمالي مساحة		269480

	نوع تصنيف	النسبة المئوية	المساحة بالفدان عام 2020
	زراعة	18%	48506
	صحراء	80%	215584
	عمران	2%	5390
	اجمالي مساحة		269480

نوع تصنيف	النسبة المئوية	المساحة بالفدان عام 2015
زراعة	12%	32338
صحراء	86%	231752
عمران	2%	5390
اجمالي مساحة		269480

المتوسطات الشهريه لعدد ساعات سطوع الشمس

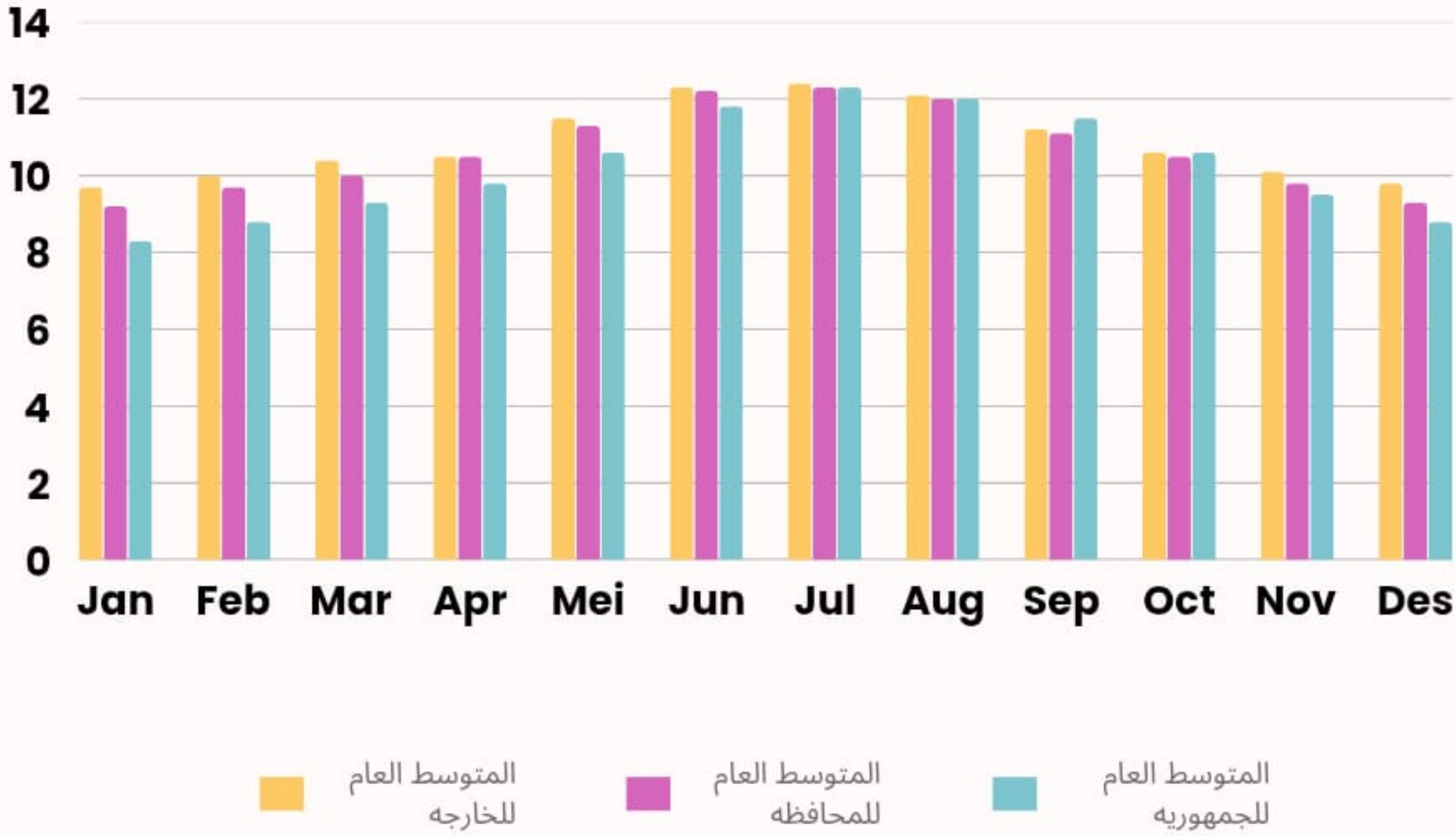

الكهرباء المولده من المحطات الكهروضوئيه فى مركز الخارجه

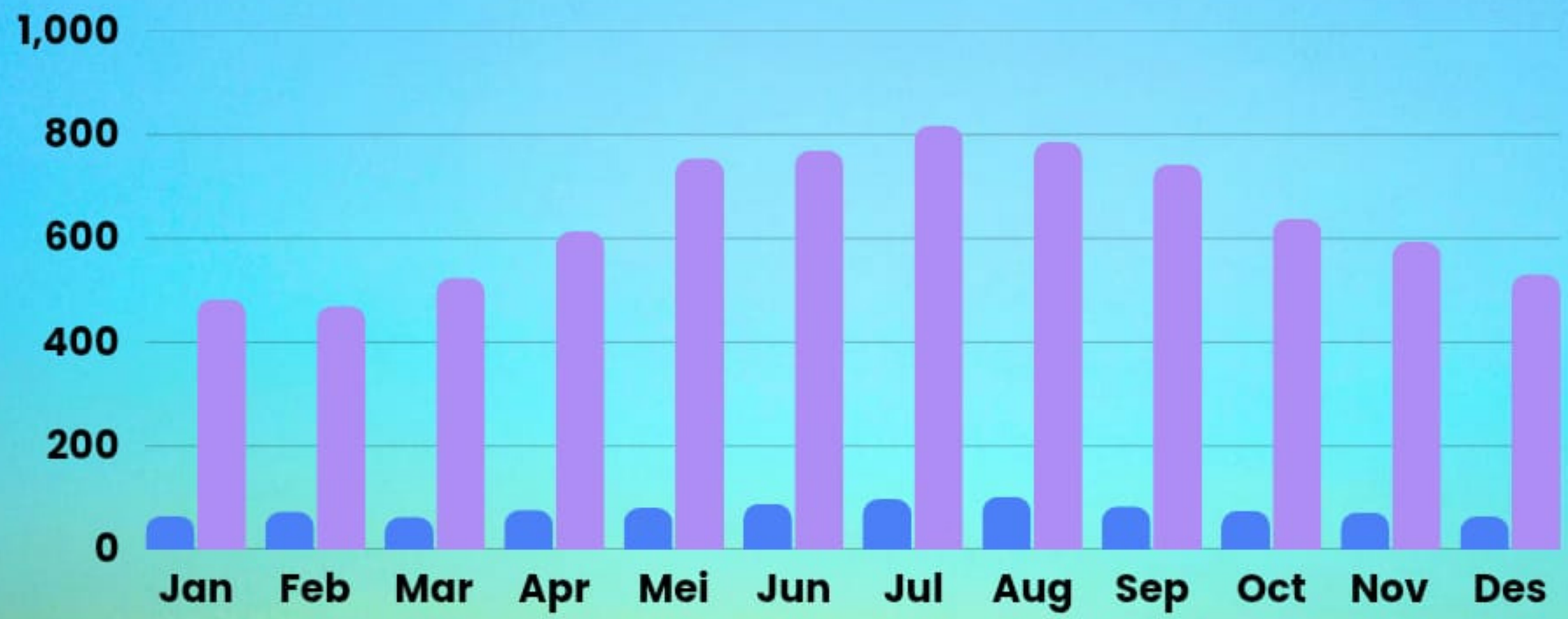

جمله المحافظه

مركز الخارجه
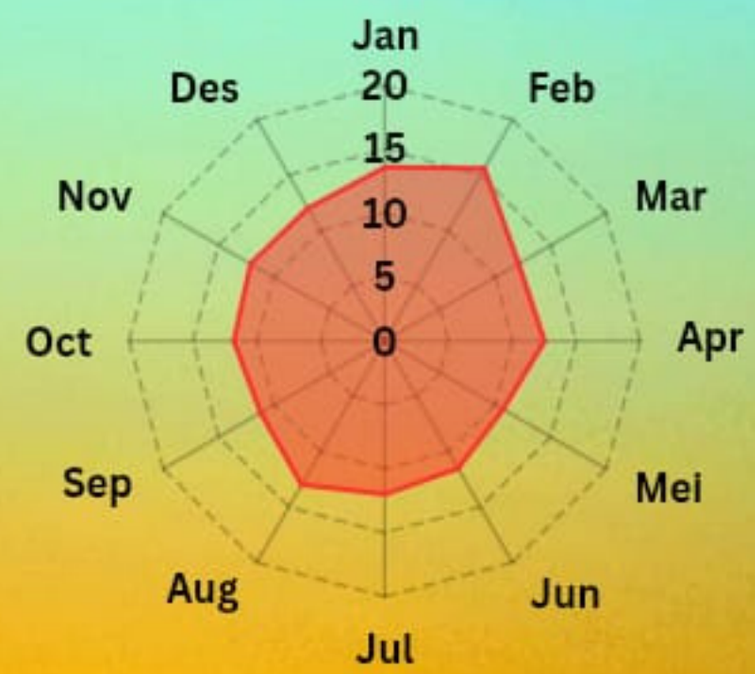
نسبه المركز